현대 오토에버 모빌리티 SW 스쿨 '스마트팩토리'

# 머신비전 프로젝트
# 실내 AR 내비게이션

TEAM 2조 KONA

박화성, 김민정, 박소윤, 김영복, 김완택

고용노동부

KOREATECH 직업능력심사평가원

K-Digital Training

# 목 차


01 사용자 시나리오

02 프로젝트 아키텍쳐

03 프로젝트 모델

01

K-Digital Training

# 사용자 시나리오



# 01

K-Digital Training

# 사용자 시나리오



# 사용자 시나리오





# 01 사용자 시나리오

K-Digital Training

@스팩 3기 김완택 사무실로 오세요



# 01

K-Digital Training

# 사용자 시나리오






01

K-Digital Training

# 사용자 시나리오




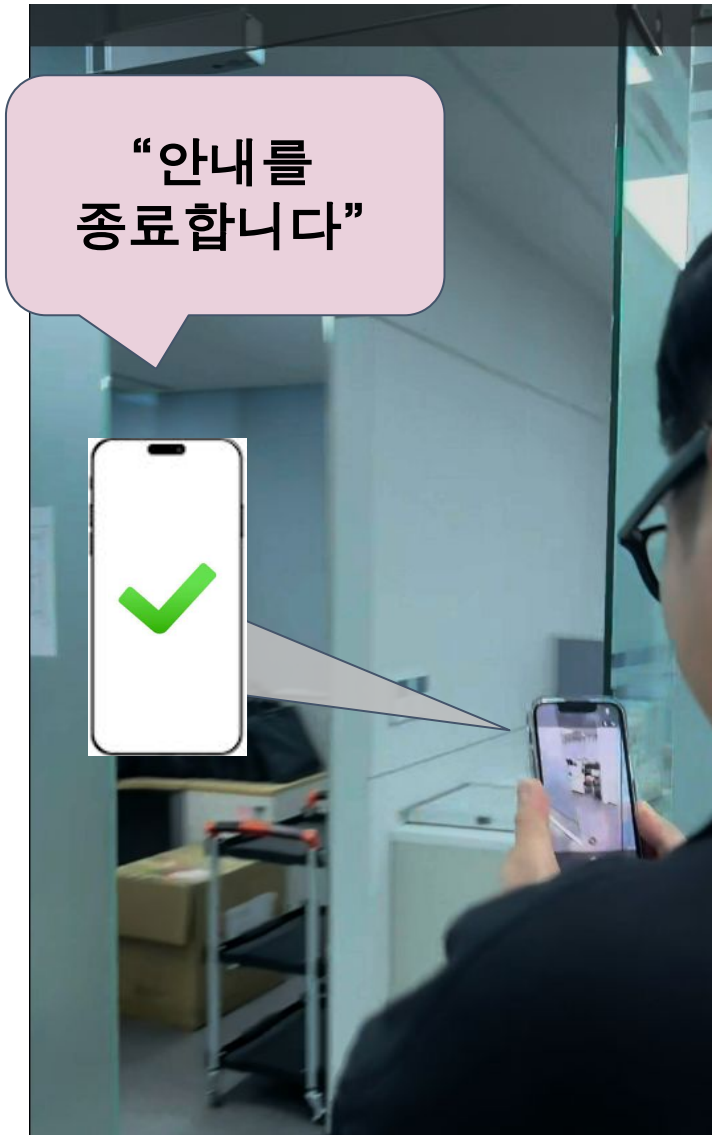

# 실시간 실내 네비게이션 시스템 아키텍쳐

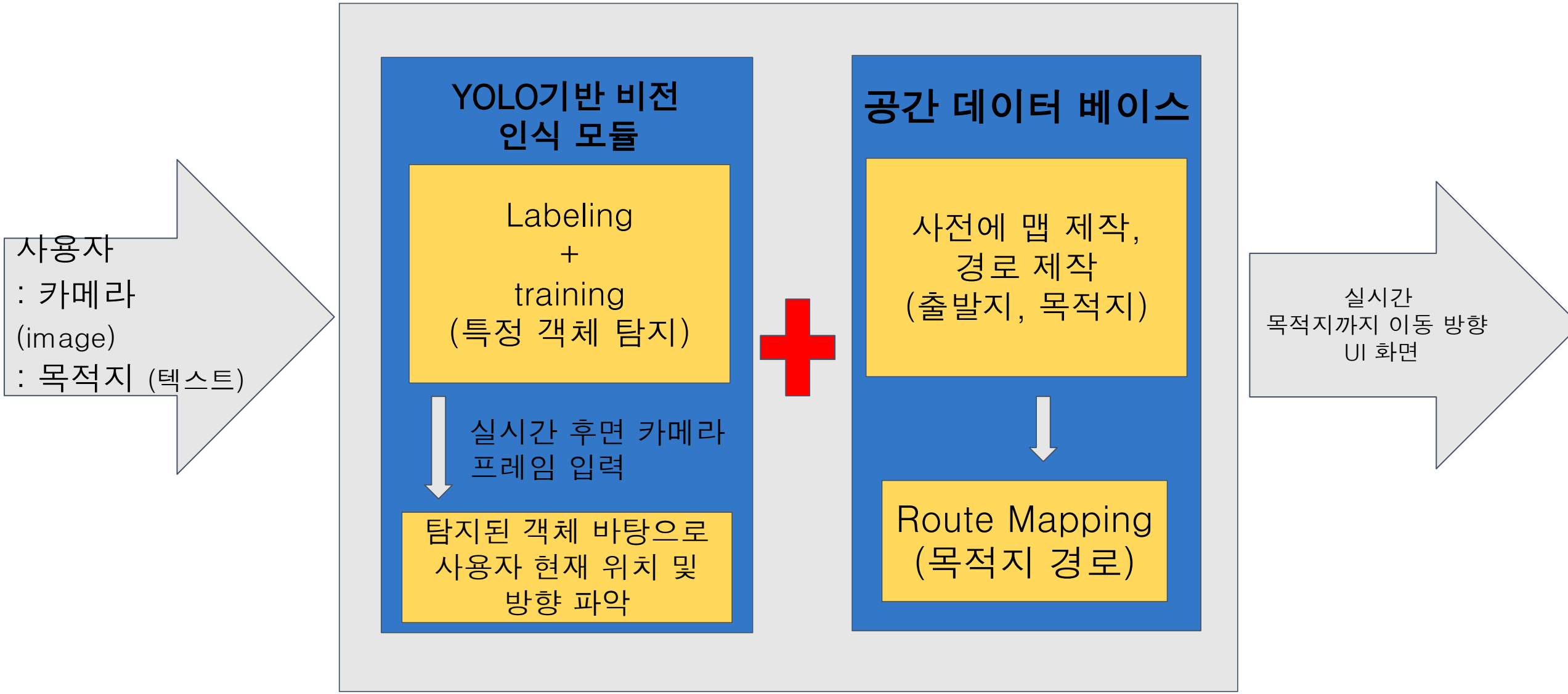

# 프로젝트 모델

* 결과 제시 ② 모델 개요

**1. 공간 데이터베이스 구축 (hloc + COLMAP)**

- 수백 장의 사진/영상에서 특징점을 추출하여 이를 3D 공간 좌표(x, y, z)로 변환하여 지도를 만든다.

**2. 내 위치 파악 (YOLO + SuperPoint + LightGlue + PnP)**

- YOLO로 대략적인 위치 파악 후, SuperPoint로 센서 없이 정밀 위치를 계산

**3. AR 길 안내(Pathfinding)**

- 목적지를 입력하면 바닥에 실시간으로 화살표 표시